Etude sur l'eau potable

Vue Mondiale | Vue Continentale | Vue Nationale

Vue mondiale

Année: 2000 – 2018

Granularité: (Tout)

G1 G2 : Granularité: Rurale, Urbaine, Totale

G3 : % Population avec un accès [...] à l'eau potable: Au moins basique, Géré de manière sûre

G1 : Evolution de la population mondiale au cours du temps

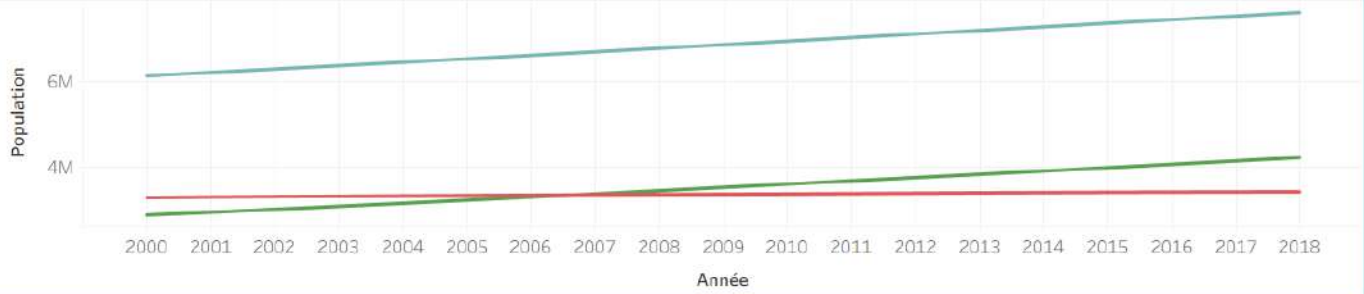

Population ayant accès à l'eau (2000-2018) :

83,89 %

Décès attribués au manque ou à l'insalubrité de l'eau (2016) :

870 366

Evolution de la population entre 2000 et 2018 :

24,22%

G2 : Pourcentage de la population ayant accès à l'eau potable selon granularité

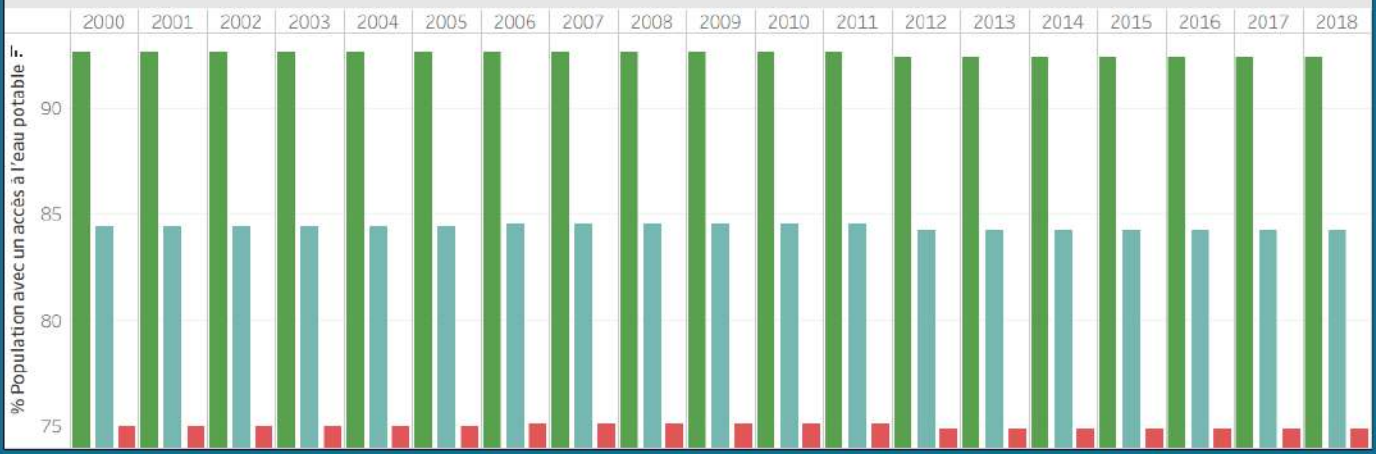

G3 : Qualité de l'accès à l'eau potable (2000-2018)

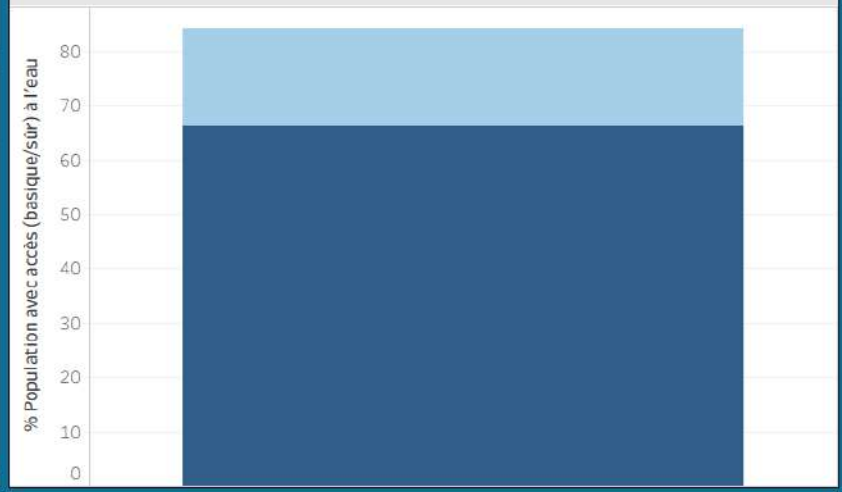

Etude sur l'eau potable

Vue Mondiale | Vue Continentale | Vue Nationale

Vue continentale

Région: (Tout)

Année: 2000 – 2018

Stabilité politique: -0,893 – 0,612

G4 : Carte mondiale de la stabilité politique

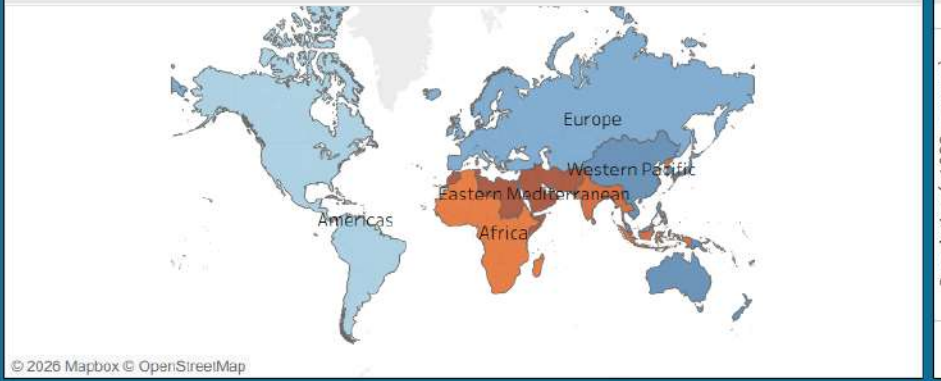

G5 : Evolution des populations rurales et urbaines

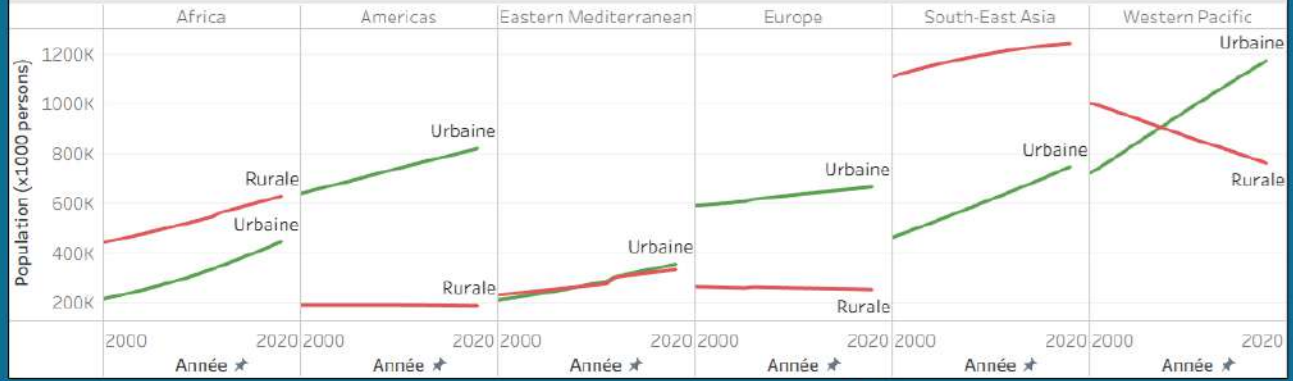

G6 : Qualité de l'accès à l'eau

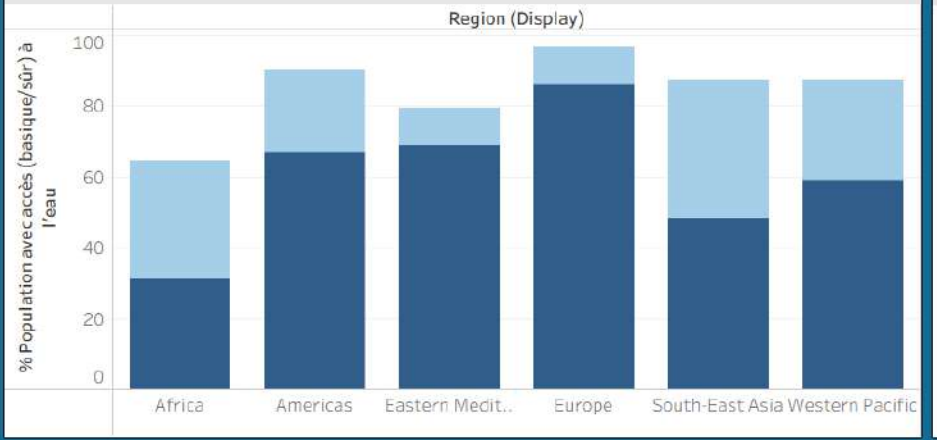

G7 : Taux de mortalité en fonction de l'accès à l'eau

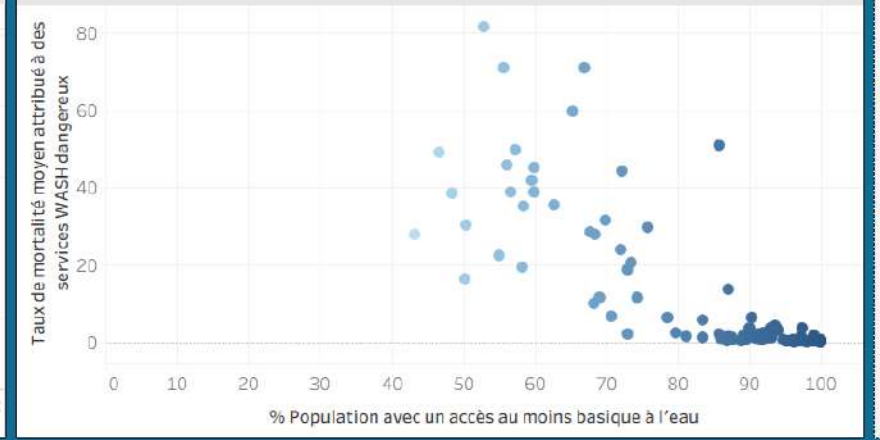

G4 : Stabilité politique

-0,893 — 0,612

G5 : Granularité de la population

- Rurale
- Urbaine

G6 : % Population avec un accès [...] à l'eau potable

- Au moins basique
- Géré de manière sûre

G7 : % Population avec un accès au moins basique à l'eau potable

43,15 — 100,00

Etude sur l'eau potable

Vue Mondiale | Vue Continentale | Vue Nationale

Vue nationale

Région
(Tout)

Pays
(Tout)

G8 : % Population avec un accès au moins basique à l'eau potable
40,33 — 100,00

G9 : Granularité
Rurale | Totale | Urbaine

G10 : % Population avec un accès [...] à l'eau potable
Au moins basique
Géré de manière sûre

G8 : Accès Basique vs Population urbaine

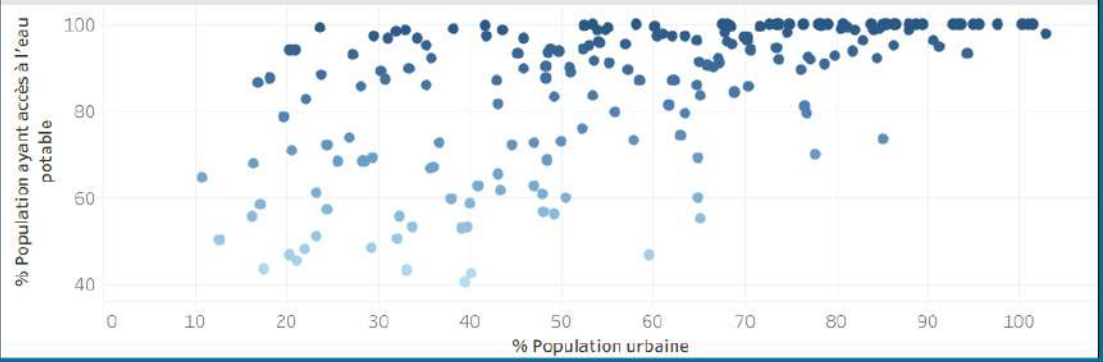

Population ayant accès à l'eau (2000-2018) :
83,89 %

Evolution de la population entre 2000 et 2018 :
24,22%

Décès attribués au manque ou à l'insalubrité de l'eau (2016) :
870 366

G9 : Evolution des populations rurales et urbaines

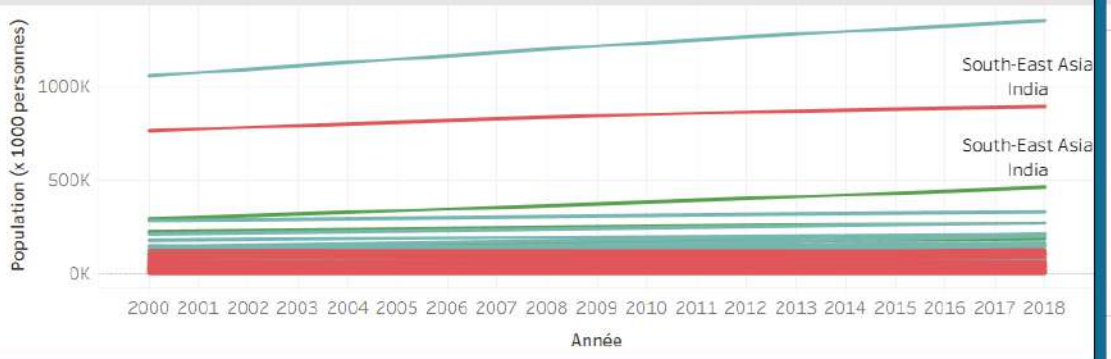
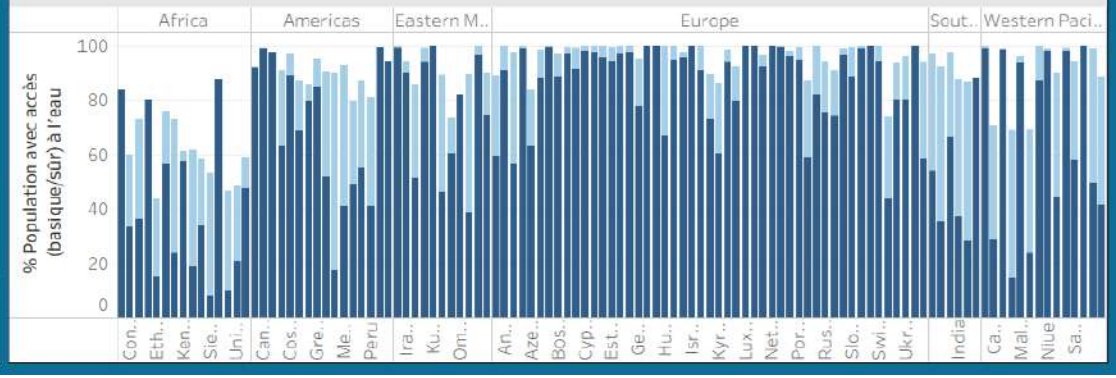
G10 : Qualité de l'accès à l'eau